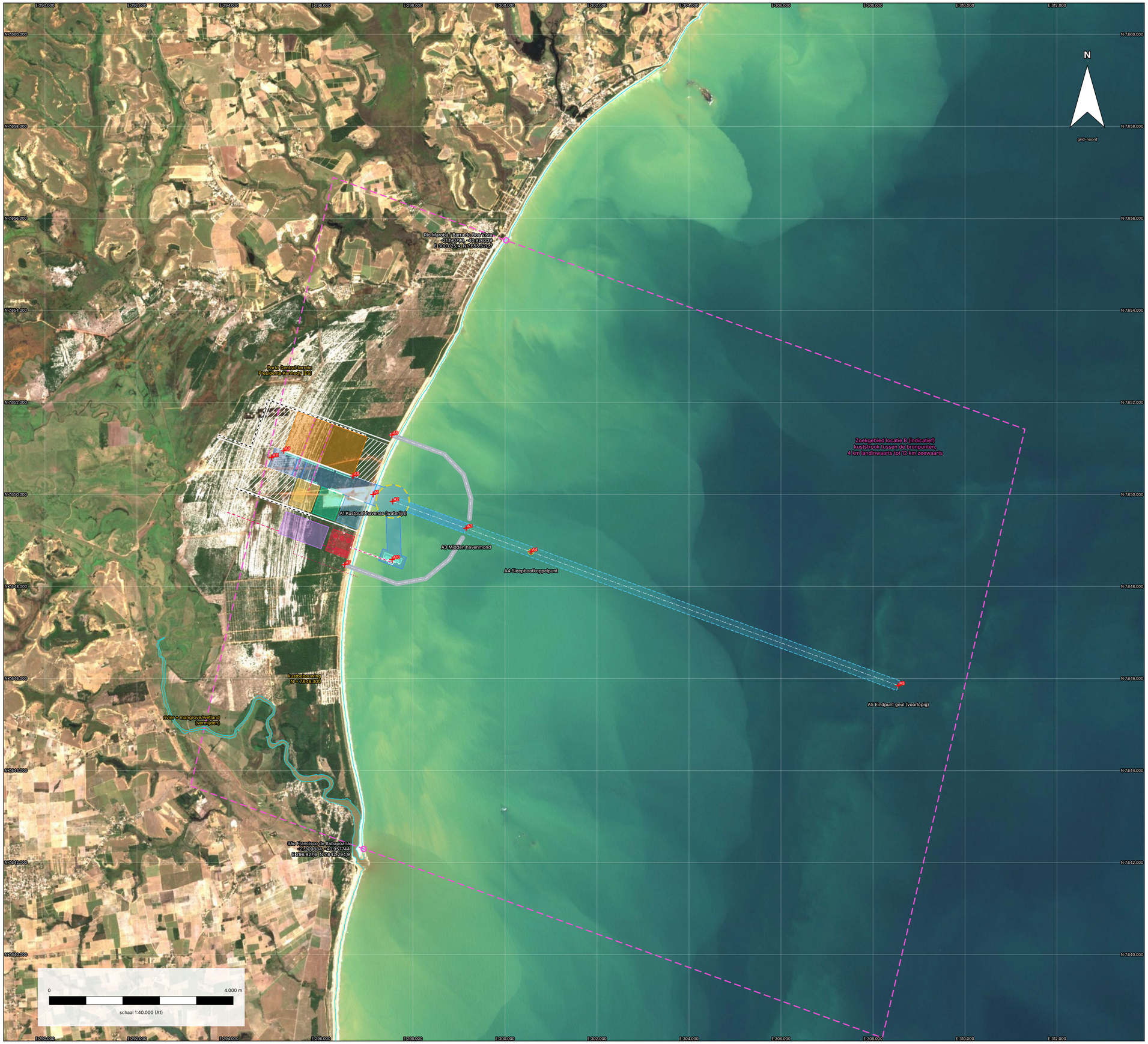


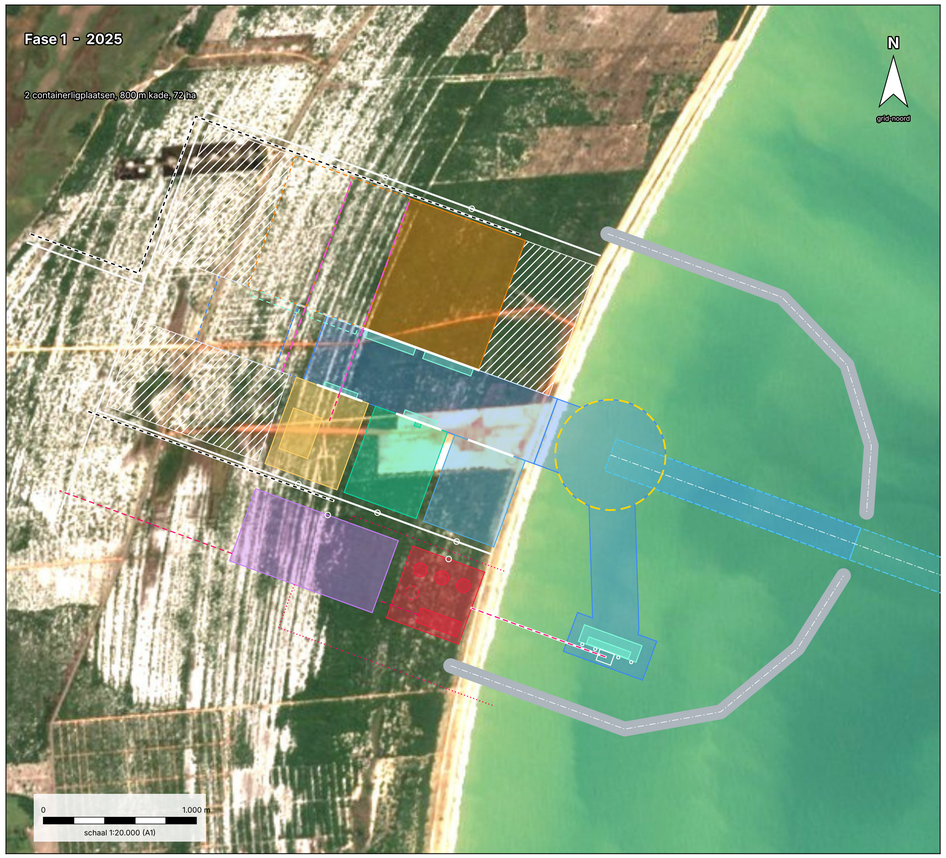
LEGENDA

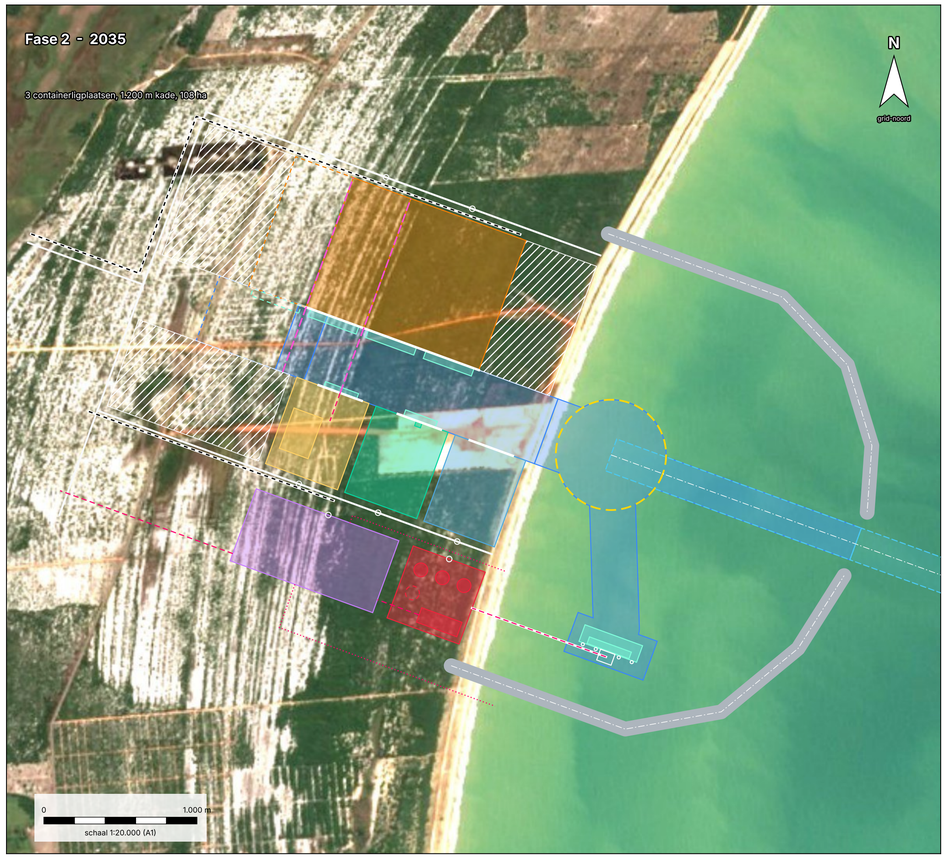
- Waterlijn 3-7-2026 (NDWI, geen MLWS-lijn)
- Zoekgebied locatie B (indicatief)
- Gebaggerd tot -18,20 m MLWS (voorlopig)
- Geul 220 m bodembreedte
- Vrije draaikom D = 720 m
- Havenmond vrij 350 m
- Golfbreker (footprint 90 m, voorlopig)
- Kade / steiger
- Scheepsenveloppe aan ligplaats
- Containerterminal
- Graanterminal
- RoRo / voertuigenterminal
- LNG-steiger, tanks en hervergassing
- Centrale + utilities (reservering)
- Havendiensten, sleepboten, loodsen
- Reserveterrein / latere uitbreiding
- Hoofdweg + terminalinritten
- Spoor
- LNG/gasleiding, koelwater (indicatief)
- Fasegrens 2025 / 2035 / 2045
- Sleepbootkoppelpunt
- Ontwerpankerpunt (E/N in maatstaat)

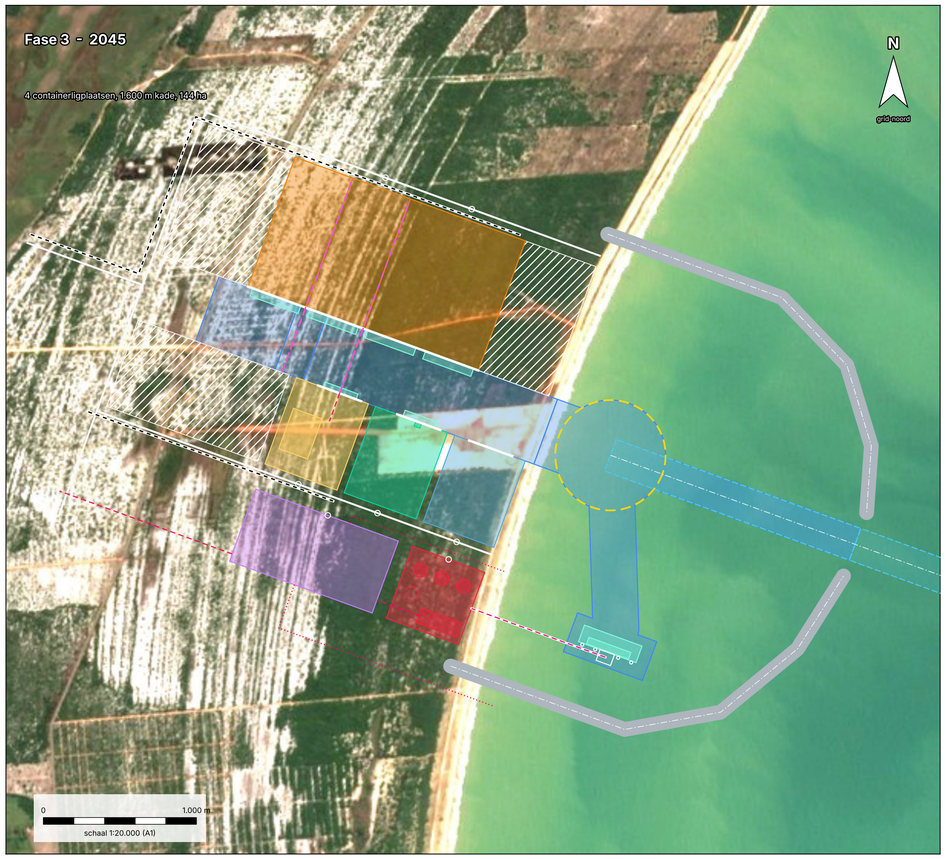
Havenligging (vastgesteld)
Porto Central, Presidente Kennedy - ES, 29350-000
Havenas haaks op de kust: azimut 110 gr (kust 20.1 gr).
A1 kustpunt: E 297.135,0 N 7.650.000,0
= -21.240329, -40.954826 (WGS84)
Havenas door het bouwterrein fase 1 aan het strand (lichte rechthoek op de luchtfoto 03-07-2026); bekkens landinwaarts op het kale Porto Central-terrein.
Georeferentiecontrole
GSHHS-kust vs. S2-waterlijn: gem. 14 m, sd 66 m (15 profielen, N 7.642-7.656 km)
Bekende afstand bronpunten: 13.582,4 m geodetisch, 13.583,8 m in grid (k = 1.00010)
Noordrichting: convergentie 0.70 gr

Project	Havenontwerp Porto Central, Presidente Kennedy (ES) - Groep 1
Module	Atelier De Haven A | NHL Stenden Civiele Techniek
Bladnaam	**Overzicht zoekgebied en havenligging**
Status	**DEFINITIEF ONTWERP (DO)**
Blad / versie	DO-01 | versie 2.0 | 22-10-2026
Schaal	1:40.000 op A1 (841 × 594 mm)
Stelsel	SIRGAS 2000 / UTM zone 24S EPSG:31984 eenheid m
Hoogtedatum	diepten in m t.o.v. MLWS, voorlopig; MLWS-DHN te verifiëren
Kaartbron	Copernicus Sentinel-2 L2A (ESA), 03-07-2026, 10 m
	tegels 24KTB/24KUB, AWS Open Data COG; geraadpleegd 22-10-2026
Kustlijn	waterlijn 03-07-2026 uit NDWI (geen MLWS-lijn)

E 294.000
E 295.000
E 296.000
E 297.000
E 298.000
E 299.000
N 7.652.000
N 7.651.000
N 7.650.000
N 7.649.000
N 7.648.000
grid-noord
Ballenmeting/inscheping
F3 2045: +1 lp, 144 ha
F2 2035: +1 lp, 108 ha
F1 2025: 2 lp, 800 m, 72 ha
Reserve logistiek
Binnenbekken F3
Binnenbekken F2
Binnenbekken F1
Reserve fase 4
Graan 40 ha
Roro 30 ha
Havendiensten/sleepboten
Centrale + utilities
LNG-tanks + hervergassing
LNG-steiger
Vlotte draaikom D 720 m
Noordelijke golfbreker
Zuidelijke golfbreker
Voorhaven + LNG-insteek
1.700 m = 5,1 LOA
SASLOG GREECE
C4
C3
C2
C1
A11
A9
A1
A3
A5
A7
A8
A10
A12
A13
A14
A15
A16
A17
A18
A19
A20
A21
A22
A23
A24
A25
A26
A27
A28
A29
A30
A31
A32
A33
A34
A35
A36
A37
A38
A39
A40
A41
A42
A43
A44
A45
A46
A47
A48
A49
A50
A51







Fasering (rekenboek Containers / Overige terminals)

Onderdeel	Fase 1 - 2025	Fase 2 - 2035	Fase 3 - 2045
Containerligplaatsen	2 (C1-C2)	3 (+C3)	4 (+C4)
Containerkade	800 m	1.200 m	1.600 m
Containerterrein	72 ha	108 ha	144 ha
Rekenvraag terrein	40,8 ha	67,9 ha	135,9 ha
Kranen per schip / totaal	3 / 6	4 / 12	5 / 20
Kadebezetting	60,0%	51,3%	63,1%
Binnenbekken gebaggerd	tot u = -1.600	tot u = -1.800	tot u = -2.350
Graan / RoRo	1 lp, 30 ha elk	equipment +	pieken toetsen
LNG	steiger + 3 tanks	doorzet 6 mln m3	8 mln m3; N-1 besluit
Centrale	eindcapaciteit	-	-
Golfbrekers + geul	volledig	onderhoud	onderhoud

Uitbreiding gebeurt landinwaarts aan het doodlopende eind van het binnenbekken: baggeren en kadebouw voor F2/F3 liggen buiten de vaarroute naar de bestaande ligplaatsen. Toekomstige onderdelen zijn gestippeld weergegeven.
Golfbrekers, geul, draaikom, LNG-steiger en leidingcorridors worden in F1 op eindmaat aangelegd (latere uitbreiding is onevenredig duur, rapport par. 10).

LEGENDA

- Waterlijn 3-7-2026 (NDWI, geen MLWS-lijn)
- Zoekgebied locatie B (indicatief)
- Gebaggerd tot -18,20 m MLWS (voorlopig)
- Geul 220 m bodembreedte
- Vrije draaikom D = 720 m
- Havenmond vrij 350 m
- Golfbreker (footprint 90 m, voorlopig)
- Kade / steiger
- Scheepsenveloppe aan ligplaats
- Containerterminal
- Graanterminal
- RoRo / voertuigenterminal
- LNG-steiger, tanks en hervergassing
- Centrale + utilities (reservering)
- Havendiensten, sleepboten, loodsen
- Reserveterrein / latere uitbreiding
- Hoofdweg + terminalinritten
- Spoor
- LNG/gasleiding, koelwater (indicatief)
- Fasegrens 2025 / 2035 / 2045
- Sleepbootkoppelpunt
- Ontwerpankerpunt (E/N in maatstaat)

Project	Havenontwerp Porto Central, Presidente Kennedy (ES) - Groep 1
Module	Atelier De Haven A | NHL Stenden Civiele Techniek
Bladnaam	**Fasering 2025 - 2035 - 2045**
Status	**DEFINITIEF ONTWERP (DO)**
Blad / versie	DO-03 | versie 2.0 | 22-10-2026
Schaal	1:20,000 op A1 (841 × 594 mm)
Stelsel	SIRGAS 2000 / UTM zone 24S EPSG:31984 eenheid m
Hoogtedatum	diepten in m t.o.v. MLWS, voorlopig; MLWS-DHN te verifiëren
Kaartbron	Copernicus Sentinel-2 L2A (ESA), 03-07-2026, 10 m
	tegels 24KTB/24KUB, AWS Open Data COG; geraadpleegd 22-10-2026
Kustlijn	waterlijn 03-07-2026 uit NDWI (geen MLWS-lijn)

Maatstaat DO - tekening tegen rekenboek

Onderdeel	Gemeten in DO-tekening	Rekenboek	Status
Hoofdgeul bodembreedte	220 m	Nautiek D20 = 220	rekenuitkomst
Bodemhoogte geul/bekken	-18,20 m MLWS	Nautiek D25 = 18,20	voorlopig
Geullengte buiten mond	10.000 m	Nautiek D31 (ingevuld)	VOORLOPIG
Vrije draaikom	D 720 m	Nautiek D28 = 720	vrij getoetst
afstand tot schepen/kades	687 / 281 m	> 0	voldoet
Havenmond vrij (footprints)	350 m	Nautiek D29 = 350	voldoet
Stopweg mond - draaikom	1.700 m	5 LOA = 1.670 m	voldoet
Sleepbootkoppelpunt	1.500 m buiten mond	rapport par. 5.1	ingetekend
Containerkade F1/F2/F3	800 / 1.200 / 1.600 m	800/1.200/1.600	gelijk
Containerterrein F1/F2/F3	72,0 / 108,0 / 144,0 ha	72/108/144 (vraag 40,8/67,9/135,9)	gelijk
Graankade / terrein	300 m / 30,0 ha	300 m / 30 ha (vraag 5,1)	gelijk
RoRo-kade / terrein	300 m / 30,0 ha	300 m / 30 ha (vraag 26,9)	gelijk
LNG-ligplaatsenvelop	400 m	ca. 400 m	dolphins indicatief
LNG-envelop tot draaikom	762 m	vrij	QRA volgt
LNG-zone (3 tanks + optie 4e)	25,0 ha	3 × 180.000 m3	N-1 open
Centrale + utilities	49,5 ha	geen vast oppervlak	reservering
Vrije breedte binnenbekken	354 m	>= 220 m	voldoet
Havenbekken baggervak (zone 1)	219,2 ha	Grondwerk C6	ingevuld
Geul buiten mond (zone 2+3)	220,0 ha	Grondwerk C7+C8	split op -15 m DHN open
Terreinophoging	307,9 ha	Grondwerk D21	ingevuld

Ontwerpankerpunten - EPSG:31984 (E/N) en WGS84 (lat/lon)

Punt	Omschrijving	E (m)	N (m)	Lat	Lon
A1	Kustpunt havenas (waterlijn)	297.135,0	7.650.000,0	-21.240329	-40.954826
A2	Middelpunt vrije draaikom	297.557,9	7.649.846,1	-21.241766	-40.950772
A3	Midden havenmond	299.155,3	7.649.264,7	-21.247194	-40.935453
A4	Sleepbootkoppelpunt	300.564,9	7.648.751,6	-21.251982	-40.921936
A5	Eindpunt geul (voorlopig)	308.552,3	7.645.844,5	-21.279096	-40.845320
A6	Wortel noordelijke golfbreker	297.540,3	7.651.289,1	-21.228734	-40.950769
A7	Wortel zuidelijke golfbreker	296.514,3	7.648.470,0	-21.254076	-40.960988
A8	Containerkade begin (F1)	296.695,1	7.650.399,5	-21.236672	-40.959015
A9	Containerkade eind (F3)	295.191,6	7.650.946,8	-21.231562	-40.973431
A10	Midden LNG-ligplaats	297.545,5	7.648.584,2	-21.253160	-40.951040
A11	Eind binnenbekken	294.926,7	7.650.803,7	-21.232824	-40.975999

Lokaal havenstelsel: oorsprong A1, u-as azimut 110 gr (zeewaarts), v-as azimut 20 gr.
E = 297.135,0 + u sin(110) + v sin(20); N = 7.650.000,0 + u cos(110) + v cos(20).
Alle maten in de DXF staan direct in projectcoördinaten; er is geen lokale verschuiving meer nodig.

Georeferentie - bronpunten en controles

Bronpunt case	WGS84	E	N	tot waterlijn
São Francisco de Itabapoana	-21.309884, -40.957744	296.927,6	7.642.294,9	18 m
Rio Marobá / Barra de Boa Vista	-21.190796, -40.926339	300.025,4	7.655.520,7	14 m

Kustlijncontrole: Sentinel-2 tegen onafhankelijke GSHHS-kust (full)

N (m)	E waterlijn S2	E kust GSHHS	dE (m)
7.642.000	296.762	296.821	58
7.643.000	296.930	296.914	-16
7.644.000	296.748	296.716	-32
7.645.000	296.570	296.527	-43
7.646.000	296.450	296.431	-19
7.647.000	296.460	296.416	-44
7.648.000	296.590	296.490	-100
7.649.000	296.818	296.829	11
7.650.000	297.136	297.126	-10
7.651.000	297.562	297.579	17
7.652.000	298.106	298.168	62
7.653.000	298.712	298.678	-34
7.654.000	299.148	299.246	98
7.655.000	299.669	299.815	146
7.656.000	300.280	300.391	111

Gemiddelde dE 13,8 m, sd 65,6 m: geen systematische verschuiving.
GSHHS heeft een nauwkeurigheid van orde 50-100 m; de spreiding past daarbij.
Bekende afstand bronpunten: geodetisch 13.582,4 m, grid 13.583,8 m,
verschil 1,38 m = schaalfactor k 1.000101 (UTM, verwacht).
Noordrichting: meridiaanconvergentie 0.70 gr; blad is grid-noord.
Bronresolutie 10 m (1 pixel). Sentinel-2 L2A wordt geleverd in WGS84/UTM 24S
(EPSG:32724); verschil met SIRGAS 2000 is < 0,1 m en verwaarloosbaar.
In Civil 3D nog te doen: drie herkenningspunten tegen Map Aerial
(GEOMAPIMAGE) meten en de afwijking in de maatstaat invullen.

Project	Havenontwerp Porto Central, Presidente Kennedy (ES) - Groep 1
Module	Atelier De Haven A | NHL Stenden Civiele Techniek
Bladnaam	**Maatstaat, ankerpunten en georeferentie**
Status	**DEFINITIEF ONTWERP (DO)**
Blad / versie	DO-04 | versie 2.0 | 22-10-2026
Schaal	n.v.t. op A1 (841 × 594 mm)
Stelsel	SIRGAS 2000 / UTM zone 24S EPSG:31984 eenheid m
Hoogtedatum	diepten in m t.o.v. MLWS, voorlopig; MLWS-DHN te verifiëren
Kaartbron	Copernicus Sentinel-2 L2A (ESA), 03-07-2026, 10 m
	tegels 24KTB/24KUB, AWS Open Data COG; geraadpleegd 22-10-2026
Kustlijn	waterlijn 03-07-2026 uit NDWI (geen MLWS-lijn)