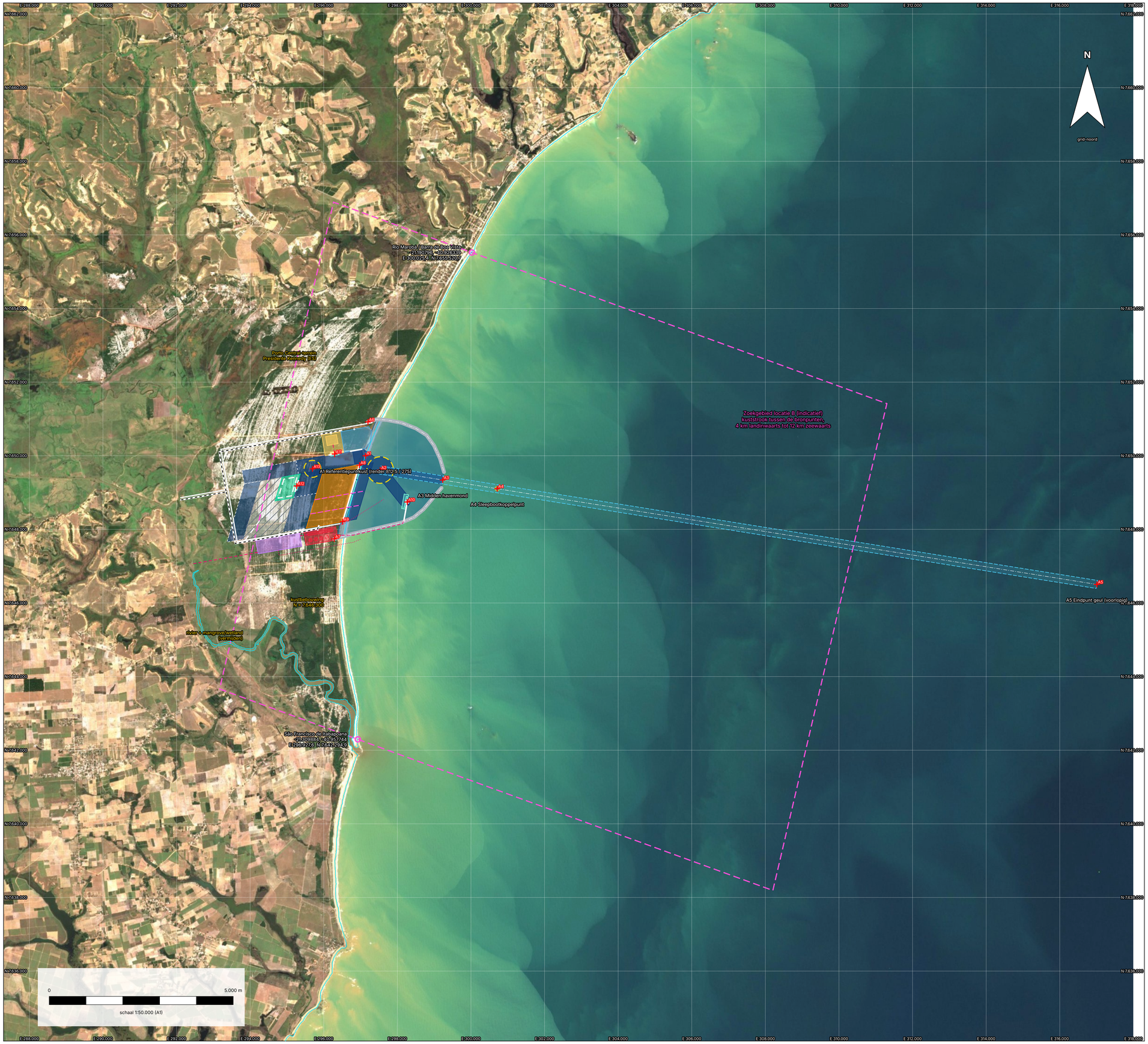


LEGENDA

- Waterlijn 3-7-2026 (NDWI, geen MLWS-lijn)
- Zoekgebied locatie B (indicatief)
- Voorhaven binnen de dammen (strandwal ontgraven)
- Gebaggerd tot -18,20 m MLWS (voorlopig)
- Geul 220 m bodembreedte
- Vrije draaikom D = 720 m
- Havenmond vrij 350 m
- Golfbreker (footprint 90 m, voorlopig)
- Kade / steiger
- Scheepsenveloppe aan ligplaats
- Containerterminal
- Graanterminal
- RoRo / voertuigenterminal
- LNG-steiger, tanks en hervergassing
- Centrale + utilities (reservering)
- Havendiensten, sleepboten, loodsen
- Reserveterrein / latere uitbreiding
- Hoofdweg + terminalinritten
- Spoor
- LNG/gasleiding, koelwater (indicatief)
- Fasegrens 2025 / 2035 / 2045
- Sleepbootkoppelpunt
- Ontwerpankerpunt (E/N in maatstaat)

Havenligging (vastgesteld)
Porto Central, Presidente Kennedy - ES, 29350-000
Havenas haaks op de kust: azimut 110 gr (kust 20.1 gr).
A1 kustpunt: E 297.135,0 N 7.650.000,0
= -21.240329, -40.954826 (WGS84)
Havenas door het bouwterrein fase 1 aan het strand (lichte rechthoek op de luchtfoto 03-07-2026); bekkens landinwaarts op het kale Porto Central-terrein.
Georeferentiecontrole
GSHHS-kust vs. S2-waterlijn: gem. 14 m, sd 66 m (15 profielen, N 7.642-7.656 km)
Bekende afstand bronpunten: 13.582,4 m geodetisch, 13.583,8 m in grid (k = 1.00010)
Noordrichting: convergentie 0.70 gr

Referentie: Porto Central render (overgetrokken voor het DO)



Overgenomen: 11/14 dammen | vingers en insteken | 6 containers | 10 graan | 7/8 RoRo
9 tankpark (LNG + centrale) | 1/8 LNG-steiger. Weggelaten (niet in opdracht): 2, 3, 5, 12, 1

Project	Havenontwerp Porto Central, Presidente Kennedy (ES) - Groep 1
Module	Atelier De Haven A | NHL Stenden Civiele Techniek
Bladnaam	**Overzicht zoekgebied en havenligging**
Status	**DEFINITIEF ONTWERP (DO)**
Blad / versie	DO-01 | versie 5.1 | 22-10-2026
Schaal	1:50.000 op A1 (841 × 594 mm)
Stelsel	SIRGAS 2000 / UTM zone 24S EPSG:31984 eenheid m
Hoogtedatum	diepten in m t.o.v. MLWS, voorlopig; MLWS-DHN te verifiëren
Kaartbron	Copernicus Sentinel-2 L2A (ESA), 03-07-2026, 10 m
	tegels 24KTB/24KUB, AWS Open Data COG; geraadpleegd 22-10-2026
Kustlijn	waterlijn 03-07-2026 uit NDWI (geen MLWS-lijn)
Peildatum	geen peiling ingelezen; bathymetrie en peildatum nog toe te voegen

E 293.000 E 294.000 E 295.000 E 296.000 E 297.000 E 298.000 E 299.000 E 300.000

N 7.652.000 N 7.651.000 N 7.650.000 N 7.649.000 N 7.648.000 N 7.647.000

N

grid-noord

Havendienst/sleepboten

Graan 30 ha

Graanhelling 300 m

Graanhelling

300 m

Noordelijke golfbreker

A1

A2

A3

A4

A5

A6

A7

A8

A9

A10

A11

A12

A13

A14

A15

A16

A17

A18

A19

A20

A21

A22

A23

A24

A25

A26

A27

A28

A29

A30

A31

A32

A33

A34

A35

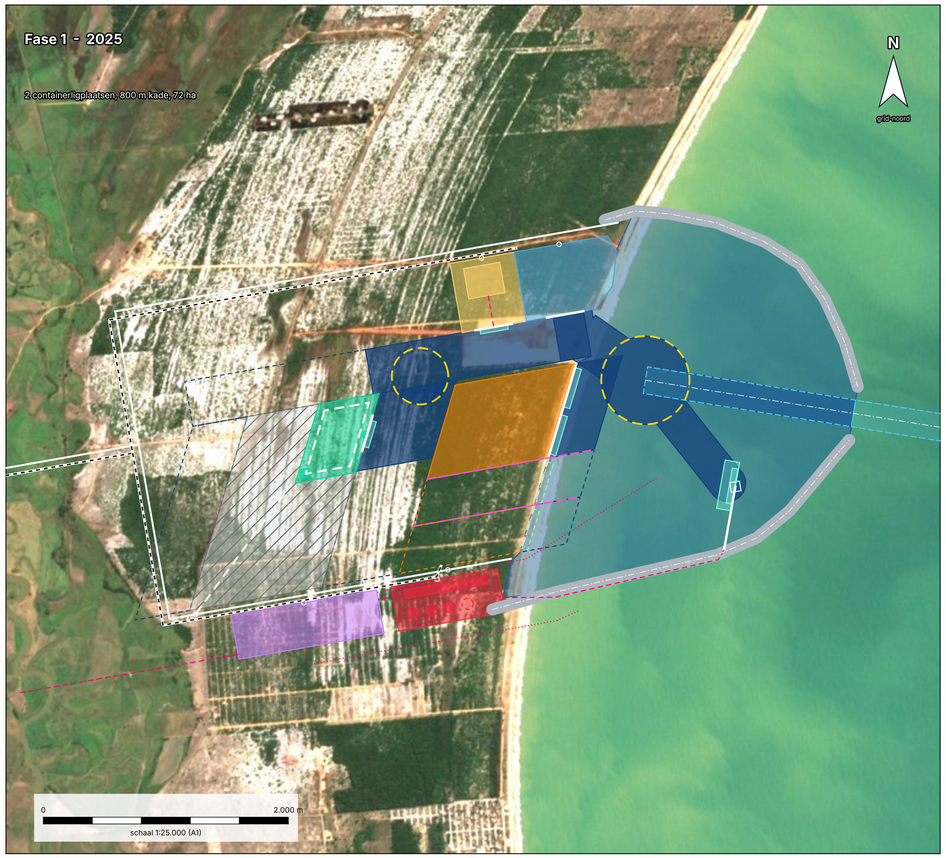
A36

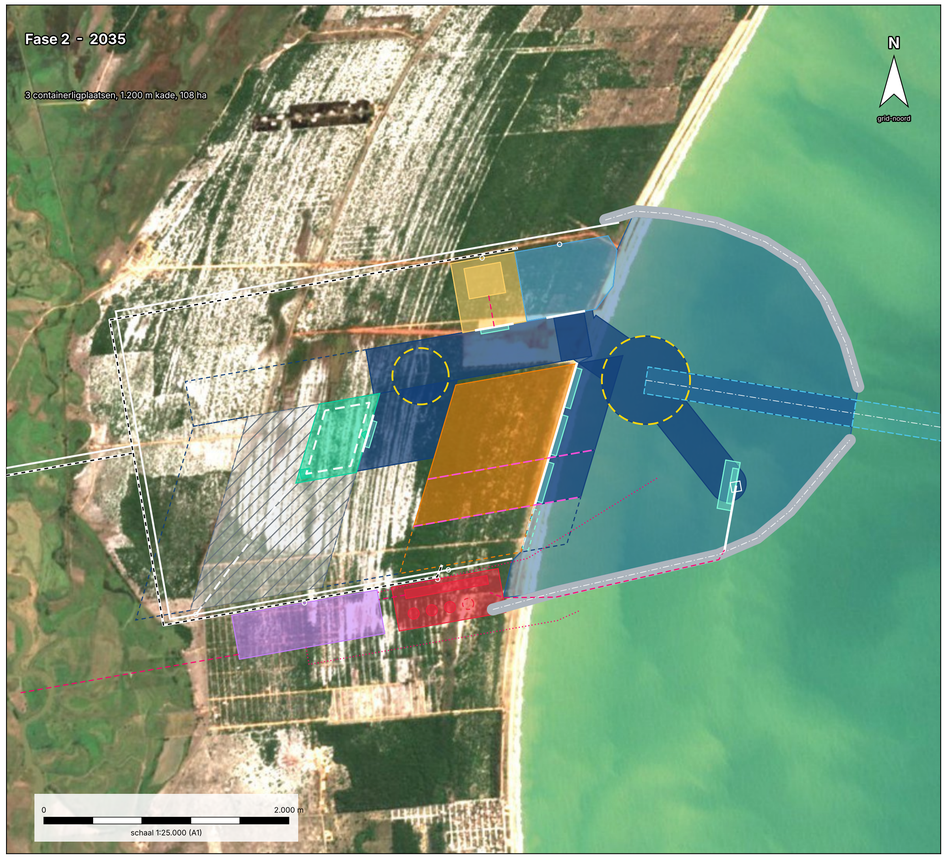
A37

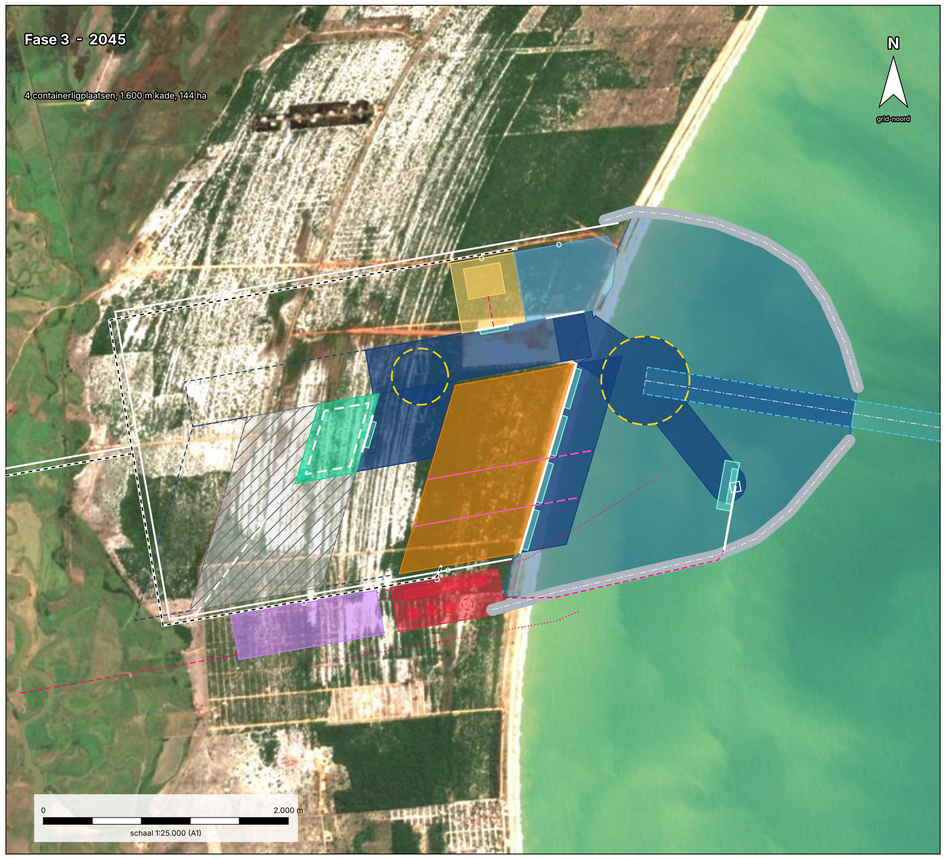
A38

A39

A40







LEGENDA

- Waterlijn 3-7-2026 (NDWI, geen MLWS-lijn)
- Zoekgebied locatie B (indicatief)
- Voorhaven binnen de dammen (strandwal ontgraven)
- Gebaggerd tot −18,20 m MLWS (voorlopig)
- Geul 220 m bodembreedte
- Vrije draaikom D = 720 m
- Havenmond vrij 350 m
- Golfbreker (footprint 90 m, voorlopig)
- Kade / steiger
- Scheepsenveloppe aan ligplaats
- Containerterminal
- Graanterminal
- RoRo / voertuigenterminal
- LNG-steiger, tanks en hervergassing
- Centrale + utilities (reservering)
- Havendiensten, sleepboten, loodsen
- Reserveterrein / latere uitbreiding
- Hoofdweg + terminalinritten
- Spoor
- LNG/gasleiding, koelwater (indicatief)
- Fasegrens 2025 / 2035 / 2045
- Sleepbootkoppelpunt
- Ontwerpankerpunt (E/N in maatstaat)

Fasering (rekenboek Containers / Overige terminals)

Onderdeel	Fase 1 - 2025	Fase 2 - 2035	Fase 3 - 2045
Containerligplaatsen	2 (C1-C2)	3 (+C3)	4 (+C4)
Containerkade	800 m	1.200 m	1.600 m
Containerterrein	72 ha	108 ha	144 ha
Rekenvraag terrein	40,8 ha	67,9 ha	135,9 ha
Kranen per schip / totaal	3 / 6	4 / 12	5 / 20
Kadebezetting	60,0%	51,3%	63,1%
Bekkens gebaggerd	hoofd-, insteek-, containerb. N	+ containerbekken midden	+ containerbekken zuid
Graan / RoRo	1 lp, 30 ha elk	equipment +	pieken toetsen
LNG	steiger + 3 tanks	doorzet 6 mln m3	8 mln m3; N-1 besluit
Centrale	eindcapaciteit	-	-
Golfbrekers + geul	volledig	onderhoud	onderhoud

De containerkade aan de voorhaven groeit zuidwaarts; baggeren en kadebouw voor F2/F3 gebeuren aan het zuideinde, buiten de vaarroute naar C1/C2 en de draaikom. Toekomstige onderdelen zijn gestippeld; alleen functies uit de opdracht zijn getekend. Golfbrekers, geul, draaikom, LNG-steiger en leidingcorridors worden in F1 op eindmaat aangelegd (latere uitbreiding is onevenredig duur, rapport par. 10).

Project	Havenontwerp Porto Central, Presidente Kennedy (ES) - Groep 1
Module	Atelier De Haven A | NHL Stenden Civiele Techniek
Bladnaam	**Fasering 2025 - 2035 - 2045**
Status	**DEFINITIEF ONTWERP (DO)**
Blad / versie	DO-03 | versie 5.1 | 22-10-2026
Schaal	1:25.000 op A1 (841 × 594 mm)
Stelsel	SIRGAS 2000 / UTM zone 24S EPSG:31984 eenheid m
Hoogtedatum	diepten in m t.o.v. MLWS, voorlopig; MLWS-DHN te verifiëren
Kaartbron	Copernicus Sentinel-2 L2A (ESA), 03-07-2026, 10 m
	tegels 24KTB/24KUB, AWS Open Data COG; geraadpleegd 22-10-2026
Kustlijn	waterlijn 03-07-2026 uit NDWI (geen MLWS-lijn)
Peildatum	geen peiling ingelezen; bathymetrie en peildatum nog toe te voegen

Maatstaat DO - tekening tegen rekenboek

Onderdeel	Gemeten in DO-tekening	Rekenboek	Status
Hoofdgeul bodembreedte	220 m	Nautiek D20 = 220	rekenuitkomst
Bodemhoogte geul/bekken	-18,20 m MLWS	Nautiek D25 = 18,20	voorlopig
Geullengte buiten mond	18.000 m	Nautiek D31 (ingevuld)	VOORLOPIG
Vrije draaikom	D 720 m	Nautiek D28 = 720	vrij getoetst
afstand tot schepen/kades	170 / 220 m	> 0	voldoet
Havenmond vrij (footprints)	350 m	Nautiek D29 = 350	voldoet
Stopweg mond - draaikom	1.720 m	5 LOA = 1.670 m	voldoet
Sleepbootkoppelpunt	1.500 m buiten mond	rapport par. 5.1	ingetekend
Containerkade F1/F2/F3	802 / 1.203 / 1.604 m	800/1.200/1.600	gelijk
Containerterrein F1/F2/F3	72,0 / 108,0 / 144,0 ha	72/108/144 (vraag 40,8/67,9/135,9)	gelijk
Graankade / terrein	300 m / 30,4 ha	300 m / 30 ha (vraag 5,1)	gelijk
RoRo-kade / terrein	300 m / 30,2 ha	300 m / 30 ha (vraag 26,9)	gelijk
LNG-ligplaatsenvelop	400 m	ca. 400 m	dolphins indicatief
LNG-envelop tot draaikom	561 m	vrij	QRA volgt
LNG-zone (3 tanks + optie 4e)	31,9 ha	3 × 180.000 m3	N-1 open
Centrale + utilities	43,5 ha	geen vast oppervlak	reservering
Vrije breedte binnenbekken	334 m	>= 220 m	voldoet
Havenbekken baggervak (zone 1)	260,6 ha	Grondwerk C6	ingevuld
Geul buiten mond (zone 2+3)	396,0 ha	Grondwerk C7+C8	split op -15 m DHN open
Terreinophoging	323,0 ha	Grondwerk D21	ingevuld

Ontwerpankerpunten - EPSG:31984 (E/N) en WGS84 (lat/lon)

Punt	Omschrijving	E (m)	N (m)	Lat	Lon
A1	Referentiepunt kust (render 812,5 / 275)	297.135,0	7.650.000,0	-21.240329	-40.954826
A2	Middelpunt vrije draaikom	297.534,6	7.649.611,9	-21.243878	-40.951023
A3	Midden havenmond	299.233,2	7.649.340,8	-21.246515	-40.934695
A4	Sleepbootkoppelpunt	300.714,4	7.649.104,3	-21.248813	-40.920454
A5	Eindpunt geul (voorlopig)	317.008,1	7.646.503,5	-21.274017	-40.763775
A6	Wortel noordelijke golfbreker	297.202,3	7.650.918,8	-21.232040	-40.954069
A7	Wortel zuidelijke golfbreker	296.285,1	7.647.740,8	-21.260634	-40.963283
A8	Containerkade noordeinde	296.970,7	7.649.746,9	-21.242597	-40.956438
A9	Containerkade zuideinde	296.513,3	7.648.209,1	-21.256432	-40.961028
A10	LNG-steigerkop	298.268,7	7.648.742,8	-21.251809	-40.944056
A11	Graankade midden	296.296,5	7.650.045,7	-21.239822	-40.962897
A12	RoRo-kade midden	295.265,7	7.649.177,7	-21.247545	-40.972930
A13	Middelpunt draaikom binnenhaven	295.694,8	7.649.644,1	-21.243381	-40.968741

Geometrie overgetrokken van de Porto Central-render (Referentie/Porto_Central_render.png), pixel (x, y omlaag):
schaal 10,035 m/px, draaiing 10,0 gr; render (812,5; 275) = A1. Kustfit: gemiddeld 31 m.
E = a x + b y + c; N = d x + e y + f met a..f in Maatstaat/maatstaat.json (render_affine).
Alle maten in de DXF staan direct in projectcoördinaten; er is geen lokale verschuiving meer nodig.

Georeferentie - bronpunten en controles

Bronpunt case	WGS84	E	N	tot waterlijn
São Francisco de Itabapoana	-21.309884, -40.957744	296.927,6	7.642.294,9	18 m
Rio Marobá / Barra de Boa Vista	-21.190796, -40.926339	300.025,4	7.655.520,7	14 m

Kustlijncontrole: Sentinel-2 tegen onafhankelijke GSHHS-kust (full)

N (m)	E waterlijn S2	E kust GSHHS	dE (m)
7.642.000	296.762	296.821	58
7.643.000	296.930	296.914	-16
7.644.000	296.748	296.716	-32
7.645.000	296.570	296.527	-43
7.646.000	296.450	296.431	-19
7.647.000	296.460	296.416	-44
7.648.000	296.590	296.490	-100
7.649.000	296.818	296.829	11
7.650.000	297.136	297.126	-10
7.651.000	297.562	297.579	17
7.652.000	298.106	298.168	62
7.653.000	298.712	298.678	-34
7.654.000	299.148	299.246	98
7.655.000	299.669	299.815	146
7.656.000	300.280	300.391	111

Gemiddelde dE 13,8 m, sd 65,6 m: geen systematische verschuiving.
GSHHS heeft een nauwkeurigheid van orde 50-100 m; de spreiding past daarbij.
Bekende afstand bronpunten: geodetisch 13.582,4 m, grid 13.583,8 m,
verschil 1,38 m = schaalfactor k 1,000101 (UTM, verwacht).
Noordrichting: meridiaanconvergentie 0.70 gr; blad is grid-noord.
Bronresolutie 10 m (1 pixel). Sentinel-2 L2A wordt geleverd in WGS84/UTM 24S
(EPSG:32724); verschil met SIRGAS 2000 is < 0,1 m en verwaarloosbaar.
In Civil 3D nog te doen: drie herkenningspunten tegen Map Aerial
(GEOMAPIMAGE) meten en de afwijking in de maatstaat invullen.

Project	Havenontwerp Porto Central, Presidente Kennedy (ES) - Groep 1
Module	Atelier De Haven A | NHL Stenden Civiele Techniek
Bladnaam	**Maatstaat, ankerpunten en georeferentie**
Status	**DEFINITIEF ONTWERP (DO)**
Blad / versie	DO-04 | versie 5.1 | 22-10-2026
Schaal	n.v.t. op A1 (841 × 594 mm)
Stelsel	SIRGAS 2000 / UTM zone 24S EPSG:31984 eenheid m
Hoogtedatum	diepten in m t.o.v. MLWS, voorlopig; MLWS-DHN te verifiëren
Kaartbron	Copernicus Sentinel-2 L2A (ESA), 03-07-2026, 10 m
	tegels 24KTB/24KUB, AWS Open Data COG; geraadpleegd 22-10-2026
Kustlijn	waterlijn 03-07-2026 uit NDWI (geen MLWS-lijn)
Peildatum	geen peiling ingelezen; bathymetrie en peildatum nog toe te voegen



LEGENDA

- Waterlijn 3-7-2026 (NDWI, geen MLWS-lijn)
- Zoekgebied locatie B (indicatief)
- Voorhaven binnen de dammen (strandwal ontgraven)
- Gebaggerd tot -18,20 m MLWS (voorlopig)
- Geul 220 m bodembreedte
- Vrije draaikom D = 720 m
- Havenmond vrij 350 m
- Golfbreker (footprint 90 m, voorlopig)
- Kade / steiger
- Scheepsenveloppe aan ligplaats
- Containerterminal
- Graanterminal
- RoRo / voertuigenterminal
- LNG-steiger, tanks en hervergassing
- Centrale + utilities (reservering)
- Havendiensten, sleepboten, loodsen
- Reserveterrein / latere uitbreiding
- Hoofdweg + terminalinritten
- Spoor
- LNG/gasleiding, koelwater (indicatief)
- Fasegrens 2025 / 2035 / 2045
- Sleepbootkoppelpunt
- Ontwerpankerpunt (E/N in maatstaat)

Controle overtrek

De render is op schaal en op de echte kust gelegd:
schaal 10,035 m per pixel, draaiing 10,0 gr;
kustlijn render tegen waterlijn: gem. 31 m.
Gekleurde lijnen = definitief ontwerp (DO).
Afwijkingen van de render zijn bewust:
- havenmond 350 m vrij (render ca. 640 m);
- alleen functies uit de opdracht: erts, werf, industrie en olie weggelaten;
- draaikom binnenhaven D 460 m op de -16 m-cirkel;
- containerkade aan de oostzijde van vinger 6: bereikbaar vanuit de draaikom zonder bocht;
- maten volgen het rekenboek.

In de DXF staat de render op laag HV-REFERENTIE (uit); aanzetten om zelf verder over te trekken.

Project	Havenontwerp Porto Central, Presidente Kennedy (ES) - Groep 1
Module	Atelier De Haven A | NHL Stenden Civiele Techniek
Bladnaam	**Overtrek Porto Central-render op luchtfoto**
Status	**DEFINITIEF ONTWERP (DO)**
Blad / versie	DO-05 | versie 5.1 | 22-10-2026
Schaal	1:12.500 op A1 (841 × 594 mm)
Stelsel	SIRGAS 2000 / UTM zone 24S EPSG:31984 eenheid m
Hoogtedatum	diepten in m t.o.v. MLWS, voorlopig; MLWS-DHN te verifiëren
Kaartbron	Copernicus Sentinel-2 L2A (ESA), 03-07-2026, 10 m tegels 24KTB/24KUB, AWS Open Data COG; gemaakt op 22-10-2026
Kustlijn	waterlijn 03-07-2026 uit NDWI (geen MLWS-lijn)
Peildatum	geen peiling ingelezen; bathymetrie en peildatum nog toe te voegen